VIGILI DEL FUOCO BOLZANO

Nucleo Droni CPVVFBZ

Drohneneinheit der BF

Istituzione del Nucleo Droni CPVVFBZ
Einrichtung der -Drohneneinheit der BF

Si comunica che dal **01.01.2025 si istituisce il Nucleo Droni** del Corpo Permanente dei Vigili del Fuoco (VVF).
Il servizio sarà **attivo H24** e sarà a supporto delle attività svolte dal Corpo Permanente dei Vigili del Fuoco di Bolzano.

Wir informieren Sie, dass **ab dem 01.01.2025 die Drohneneinheit** der Berufsfeuerweher eingerichtet wird.
Der Dienst wird **24 Stunden am Tag aktiv sein** um die Tätigkeit der BF zu unterstützen.

Competenze del Nucleo Droni
Drohnen-Kernfähigkeiten

Il personale abilitato é indicato nel documento di riferimento allegato
“MANUALE DELLE OPERAZIONI”
Il servizio di norma verrà effettuato con i droni DJI Mini 4 Pro.

Das befähigte Personal ist im beigefügten Dokument
„Handbuch der Tätigkeiten“ angegeben.

Der Dienst wird normalerweise mit DJI Mini 4 Pro-Drohnen durchgeführt.

Richiesta di Intervento
Einsatz

I Vigili del Fuoco volontari dell'Alto Adige potranno richiedere l'intervento del Nucleo Droni del Corpo Permanente di Bolzano.
La partecipazione del Corpo Permanente sarà limitata a **interventi di competenza del Servizio Antincendio.**

In particolare, il **Nucleo Droni sarà coinvolto** per:

Sopralluoghi di Polizia Giudiziaria – Gerichtpolizeiliche Aufgaben

Raccolta di documentazione fotografica e video - Sammlung von Foto- und Videodokumentationen

PER TUTTO IL RESTO CHIEDERE INDICAZIONI AL COMANDANTE

Documentazione di Riferimento - Referenzdokumentation

"MANUALE DELLE OPERAZIONI"
Tutti i membri del Nucleo Droni sono tenuti a operare secondo le indicazioni riportate la suo interno.

„TÄTIGKEITSSHANDBUCH“
Alle Mitglieder der Drohneneinheit sind verpflichtet, die darin enthaltenen Anweisungen zu befolgen.

"MANUALE DELLE OPERAZIONI"
„TÄTIGKEITSSHANDBUCH“

1.5 FUNZIONE E AMBITO DI APPLICAZIONE DI QUESTO MANUALE DELLE OPERAZIONI

ll manuale contiene le informazioni e le procedure basiche e trasversali alla tipologia di UAS e di scenario necessarie ad una condotta in sicurezza delle operazioni sia in volo che a terra.

Queste procedure denominate Standard Operating Procedures (SOP - Procedure Operative Standard) devono essere utilizzate da piloti, istruttori e personale in addestramento.
Le procedure contenute in questo manuale descrivono le operazioni nella categoria OPEN e SPECIFIC negli scenari standard (IT-STS-01, IT-STS-02) e le operazioni indoor.

"MANUALE DELLE OPERAZIONI"
„TÄTIGKEITSSHANDBUCH“

2. DESCRIZIONE GENERALE DELL’ORGANIZZAZIONE DELL’OPERATORE

2.2 MISSION

Scopo del CORPO PERMANENTE VIGILI DEL FUOCO è l'uso dei mezzi UAS per effettuare operazioni specializzate. Queste possono essere: ATTIVITA’ DI POLIZIA GIUDIZIARIA, RACCOLTA FOTO E DOCUMENTAZIONE in caso DI INCIDENTI RILEVANTI, ATTIVITÀ DI RICERCA PERSONA IN AMBITO FLUVIALE E TERRESTRE, identificazione del pericolo in caso di INTERVENTI NBCR, MONITORAGGIO inerente alla pianificazione in caso di LOTTA ALL’INCENDIO BOSCHIVO, MONITORAGGIO SPEDITIVO 2D, MAPPATURA E MODELLIZZAZIONE 3D ed ogni possibile operazione specializzata con UAS legata ai compiti di istituto.

"MANUALE DELLE OPERAZIONI"
„TÄTIGKEITSSHANDBUCH“

2.4.1. ORGANIGRAMMA GENERALE DELL'OPERATORE

RUOLO	NOME
Direttore delle Operazioni	ING. ALBER
Responsabile Tecnico	I.A.C. FELIS GIUSEPPE
Responsabile dell’Addestramento	C.S. BOLDRIN
Responsabile della Manutenzione	I.A. TAMMERLE

"MANUALE DELLE OPERAZIONI"
„TÄTIGKEITSSHANDBUCH“

2.7.1. AUTORITA' DEL PILOTA IN COMANDO

ll pilota in comando esercita piena autorità sulle operazioni UAS. Dovrà quindi impiegare tutte le precauzioni per mantenere un alto livello di sicurezza sia con UAV a terra che in volo. Ha inoltre autorità sul personale di supporto, che dovrà quindi seguire tempestivamente le sue istruzioni.

È privilegio e dovere del PIC prendere la decisione finale sull’utilizzo o meno del UAS e sulla valutazione di tutti gli elementi che incidono sulle condizioni di volo alla luce della normativa vigente e al fine di garantire la sicurezza sua, del personale presente e per persone e cose nei dintorni dell'area delle operazioni

Le categorie di volo

In totale le categorie di volo con un veicolo UAS sono 3:

OPEN

Operazioni a basso rischio

- Nessun requisito particolare richiesto

SPECIFIC

Operazioni ad alto rischio

- Richiesta autorizzazione dalle autorità competenti prima di volare

CERTIFIED

Operazioni con il più alto valore di rischio

- Le autorità competenti devono approvare l'operatore
- Licenza da pilota remoto
- UAS certificato

In questa presentazione si tratterà esclusivamente della categoria «OPEN»

Categoria OPEN

- Operazioni a basso rischio
- Si suddivide in 3 sotto-categorie:

A1

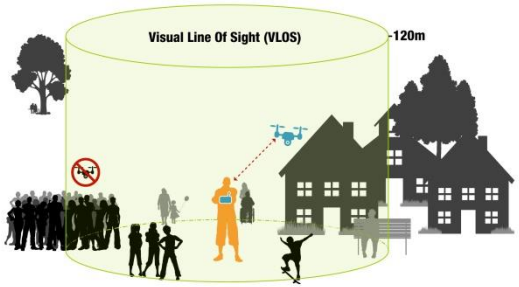

- Massa drone < 900 g;
- Drone in VLOS;
- SI, volo „vicino“ alle persone;
- NO, volo su assembramenti di persone;

A2

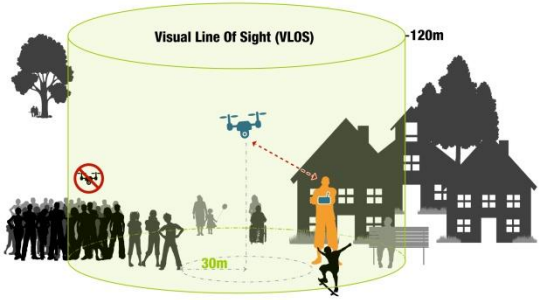

- Massa drone < 4 kg;
- Drone in VLOS;
- Velocitá inferiore 5 m/s
- EVITARE volo „vicino“ alle persone
- NO, volo su assembramenti di persone;

A3

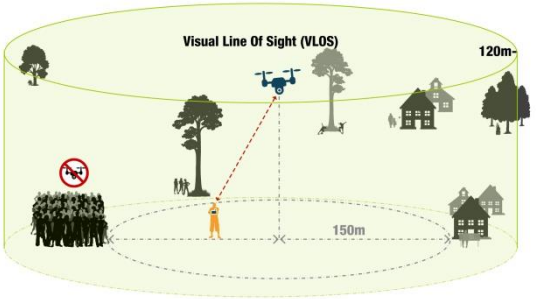

- Massa drone < 25 kg;
- Drone in VLOS;
- Distanza < di 150 m da zone urbane, commerciali, industriali;
- NO, volo „vicino“ alle persone;
- NO, volo su assembramenti di persone;

Categoria SPECIFIC

↓

3.1.2 RISCHI ASSOCIATI ALLE OPERAZIONI “SPECIFIC” IN SCENARIO STANDARD

Tutte le operazioni nelle quali non sono rispettati i requisiti delle “OPEN”, sono da considerare “SPECIFIC”.

Nel presente Manuale sono descritte unicamente le “SPECIFIC” condotte in SCENARI STANDARD.

Nelle OPERAZIONI “SPECIFIC” effettuate in SCENARI STANDARD, l’analisi del rischio è stata preventivamente effettuata dall’ENAC sulla base della metodologia SORA e pertanto non è richiesto che sia effettuata dall’operatore.

Zona ROSSA
Parchi – autorizzati

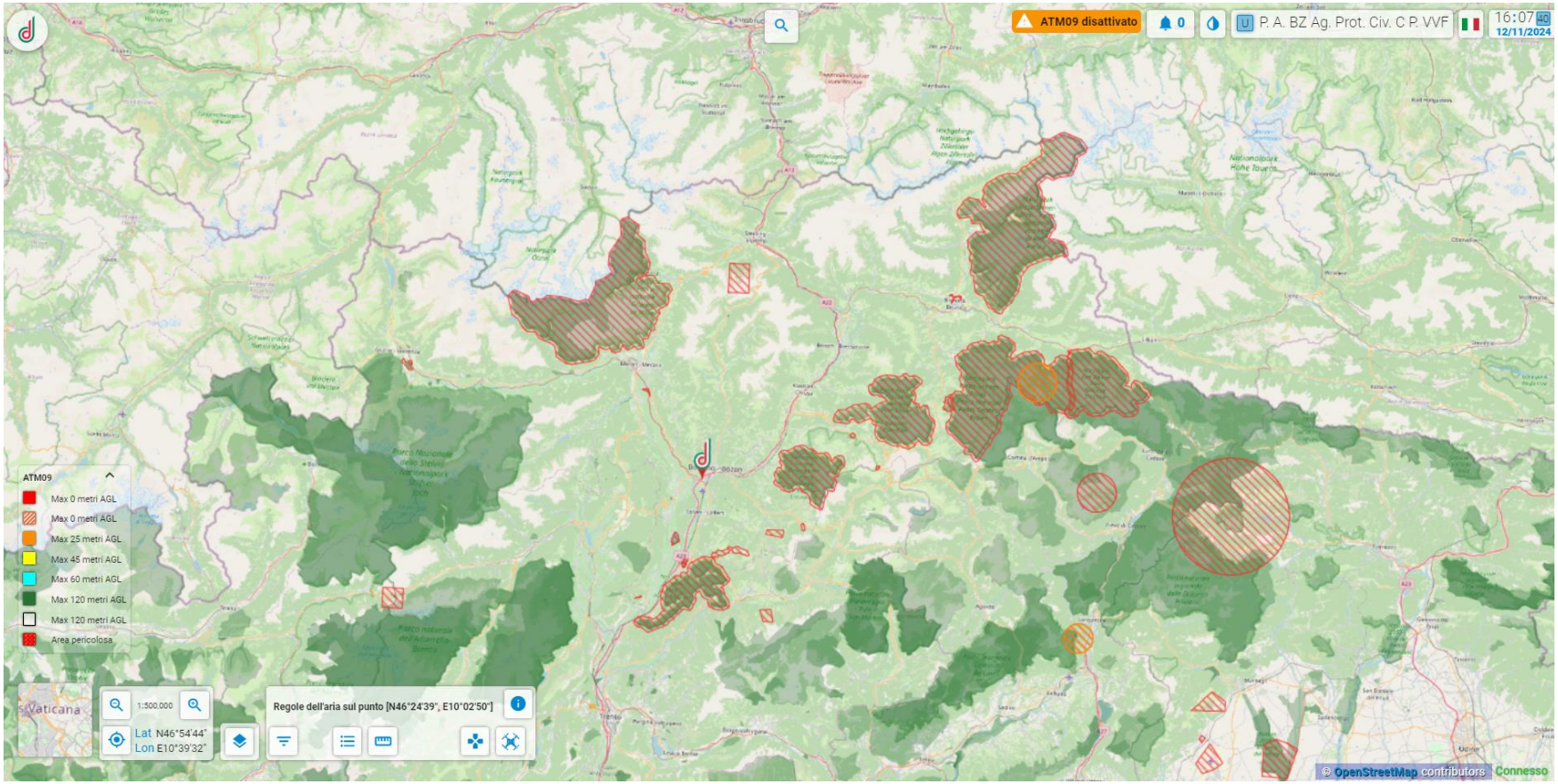

3.2.iii VOLO IN AREA ROSSA AEROPORTUALE CIVILE IN ASSENZA DI AUTORIZZAZIONE

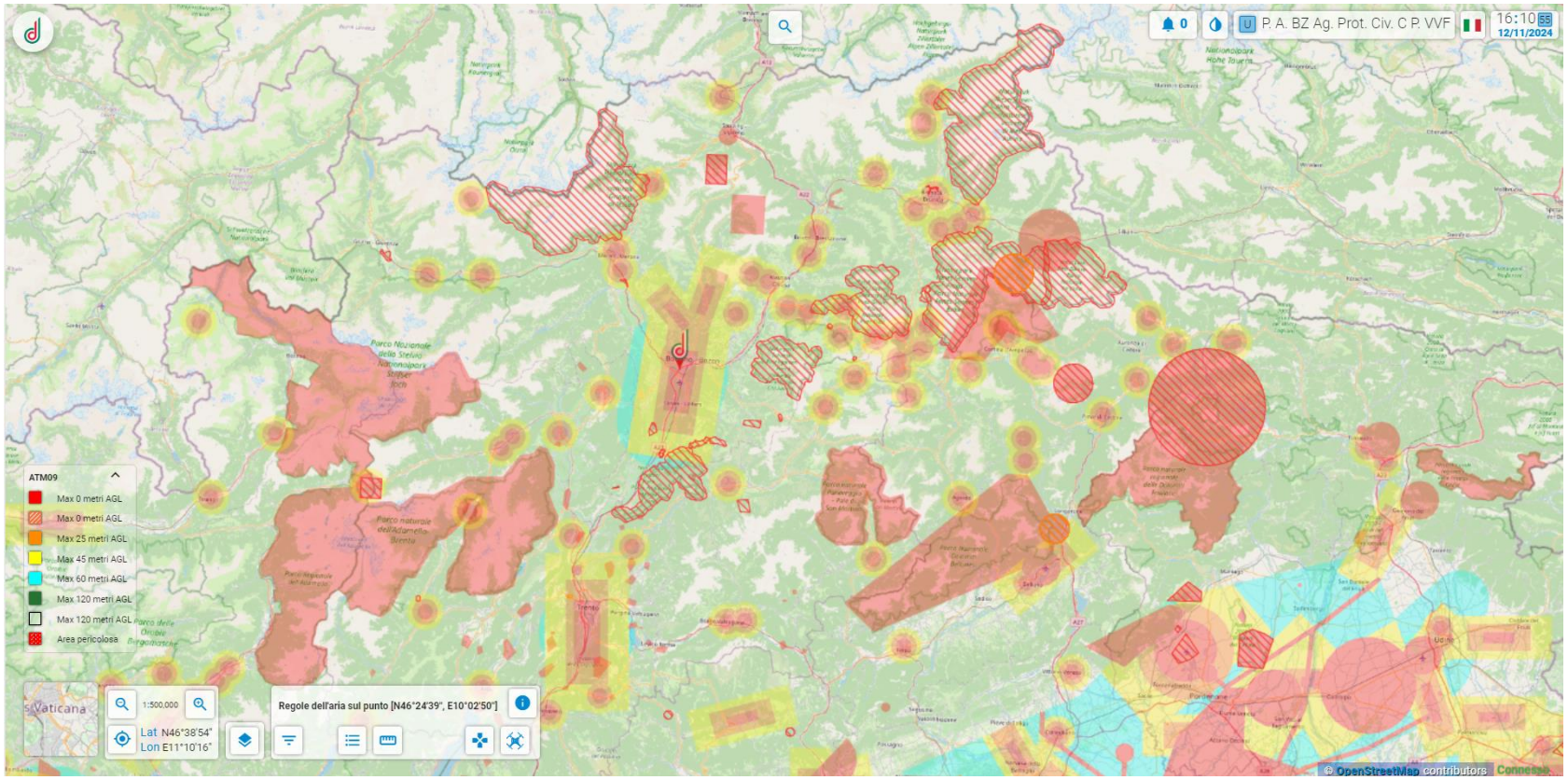

Zona ROSSA
ATZ?

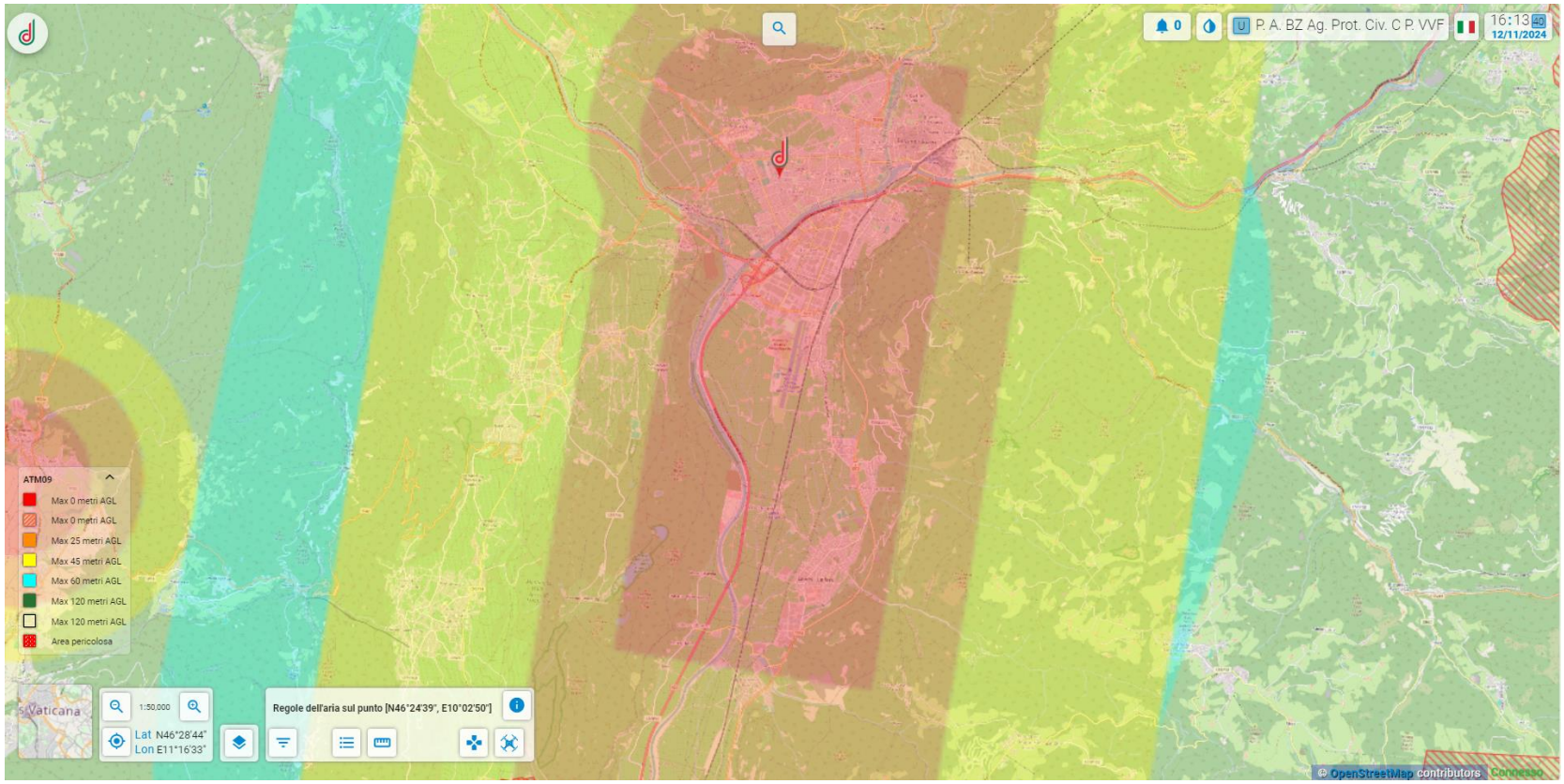

2) **MODIFICA PARAGRAFO 6.4 DELLA CIRCOLARE ATM-09A**

*"Nelle aree rosse **sono possibili operazioni UAS nell'intorno di un ostacolo artificiale entro 10 mt orizzontalmente e fino a 3 mt verticalmente**, con l'esclusione della zona sovrastante il sedime aeroportuale o le infrastrutture aeroportuali, ampliata di un buffer, in senso orizzontale, di **500 mt**. Tali operazioni rimangono in categoria specifica (possono quindi essere condotte in accordo a uno scenario standard oppure a fronte di una autorizzazione operativa rilasciata da ENAC).*

Quanto riportato nel presente capoverso non si applica nelle aree rosse definite nelle vicinanze degli aeroporti militari.

*In ogni caso, **è responsabilità dell'operatore dell'UAS ottenere il preventivo permesso del proprietario/responsabile dell'ostacolo in oggetto** (rif.: Reg. 2019/947: GM UAS.OPEN.0103)."*

Recentemente la modifica di cui sopra ha aperto nuove possibilità di sorvolo in area rossa di tipo aeroportuale in quanto **ha eliminato la necessità di chiedere il nulla osta a ENAC qualora si verifichino le seguenti condizioni**:

1) L'operazione UAS avvenga **nell'intorno di un ostacolo artificiale entro 10 mt orizzontalmente e fino a 3 mt verticalmente**;

2) L'operazione UAS **non avvenga nella zona sovrastante il sedime aeroportuale o le infrastrutture aeroportuali, ampliata di un buffer, in senso orizzontale, di 500 mt**;

3) La zona rossa interessata NON sia a protezione di un aeroporto militare;

4) Sia stato preventivamente **ottenuto il preventivo permesso del proprietario/responsabile dell'ostacolo in oggetto**; Per il Corpo Permanento in intervento questo viene considerato come ottemperato

Zona ATZ ROSSA
FUORI dal BUFFER 500 mt

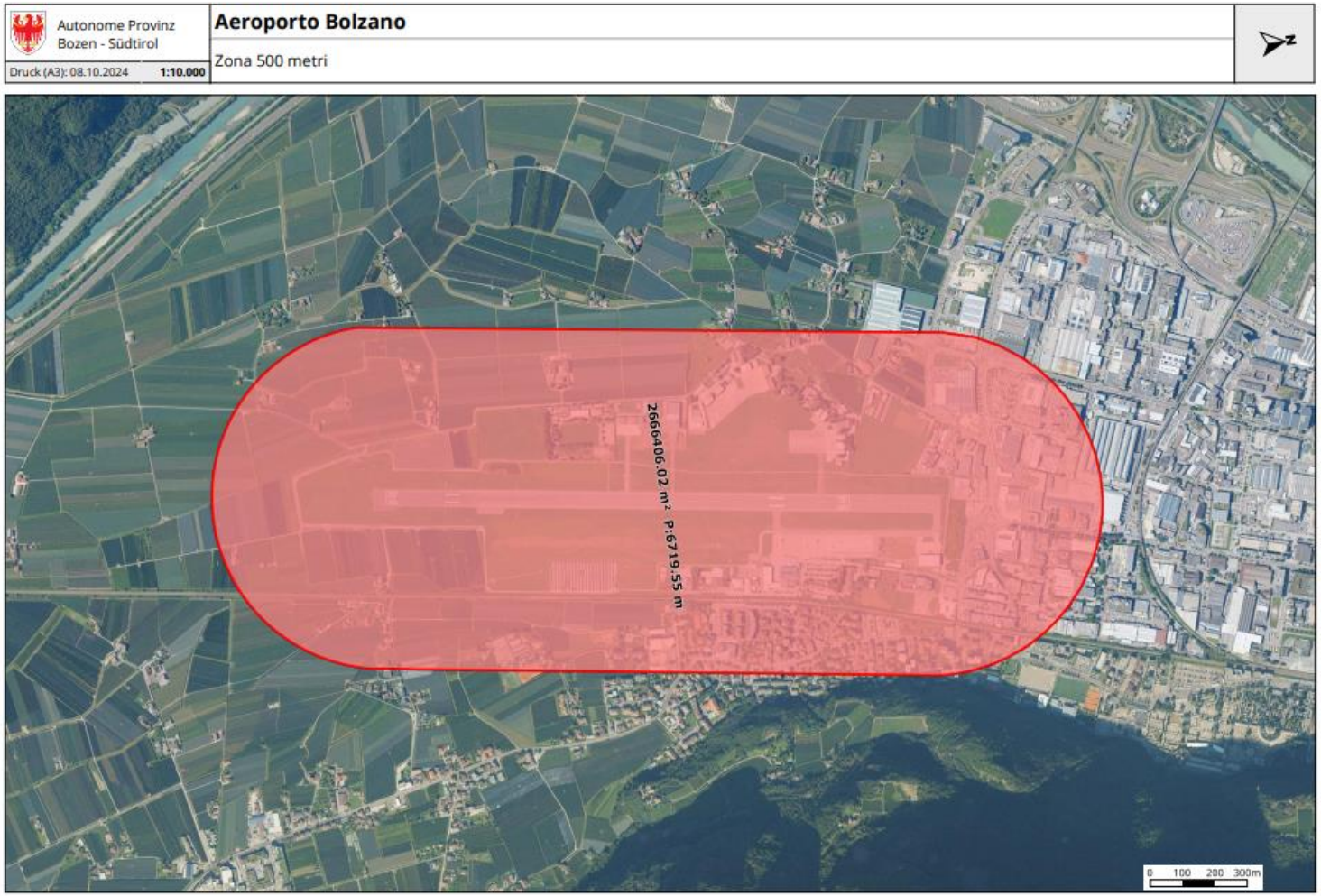

FUORI DAL BUFFER DI 500 mt

Al di fuori dei 500 dall´aeroporto pur rimanendo all'interno della zona rossa aeroportuale, è possibile operare senza autorizzazione rispettando queste indicazioni:

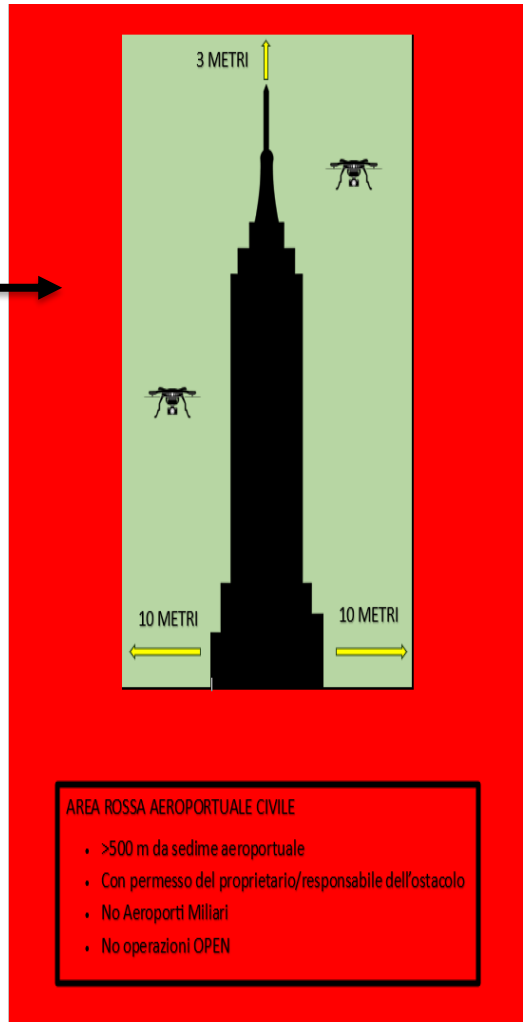

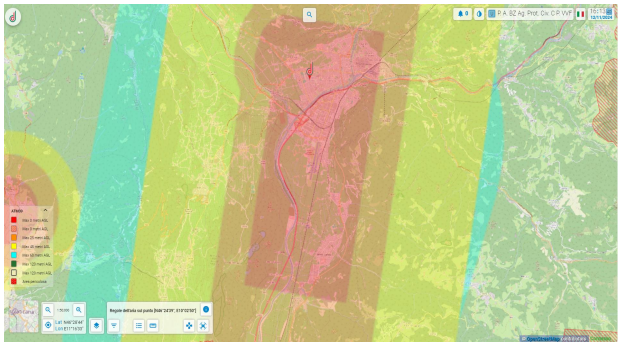

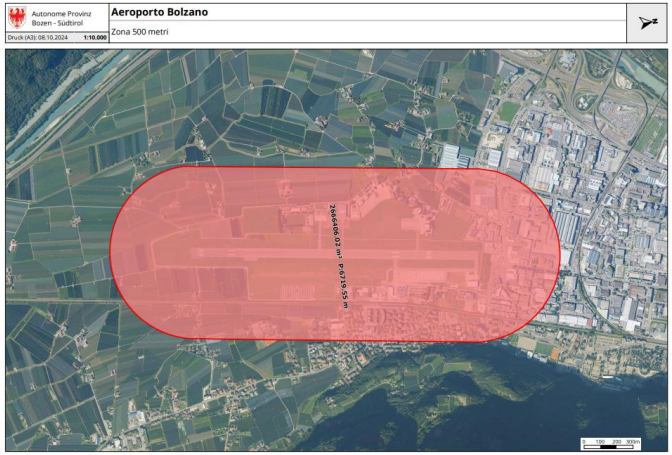

Si opera secondo gli scenari STANDART. Tutti i piloti del CPVVFBZ sono abilitati.

L'AREA DI BUFFER - 25 metri il raggio minimo

DELIMITAZIONE MINIMA

A 25 MT dall´area punto di volo